GOBIERNO DE ESPAÑA | MINISTERIO DE TRANSPORTES Y MOVILIDAD SOSTENIBLE | INSTITUTO GEOGRÁFICO NACIONAL

Red de Infraestructuras Geodésicas

Subdirección General de Astronomía y Geodesia

Reseña de Señal de Nivelación

11-abr-2026

Situación Geográfica:

Número: **931001**

Nombre: **SSC5**

Línea o Ramal: **931. Línea Anaga - Tres de Mayo**

Municipio: Santa Cruz de Tenerife

Provincia: Santa Cruz de Tenerife (Isla de Tenerife)

Hoja MTN50: 1090

Señal: Secundaria **En posición:** Vertical

Señalizada: 01 de mayo de 1983

Nivelada: 01 de enero de 2003

Enlaces:

Anterior: 931 - NGR331 (Anaga)*

Posterior: 931002 - NGR332®

Agrupada con:

Datos Geodésicos:

Altitud ortométrica: 28,5925 m.

Geopotencial: 28,0034 u.g.p.

Gravedad en superficie: 979394,79 mgals. *Observada*

Cálculo:

Coordenadas GeogrA¡ficas REGCAN95:

SEÑAL DESAPARECIDA

2024-04-13: Desaparecido.

Longitud: - 16° 14' 56"

Latitud: 28° 29' 33"

Altitud elipsoidal:

Precisión: ± (1 m - 10 m.)



Reseña:

Situada en la población de Santa Cruz de Tenerife, en el extremo N. de una meseta sobre la acera del Bar Mallorquín, al S. de la calle Méndez Núñez y junto a un murete de entrada a la casa nº 116, según croquis.

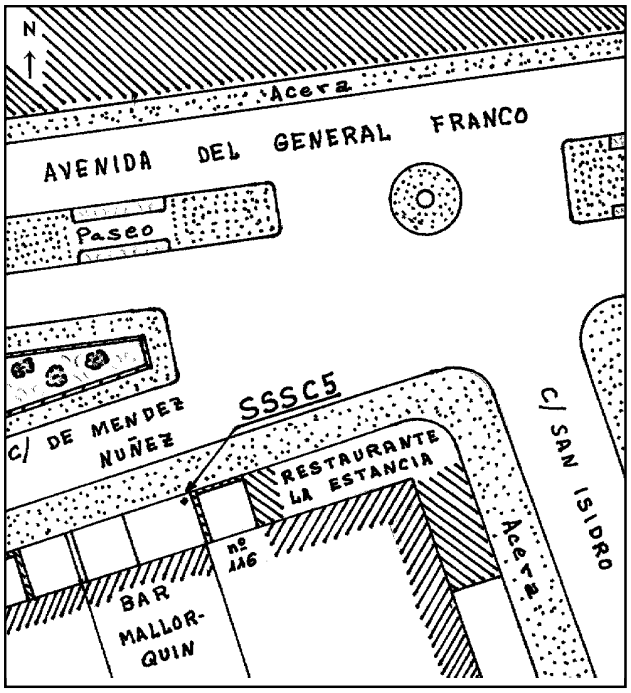

Observaciones:

Informe del estado de la Señal en: InfoRN.pdf

GOBIERNO DE ESPAÑA | MINISTERIO DE TRANSPORTES Y MOVILIDAD SOSTENIBLE | INSTITUTO GEOGRÁFICO NACIONAL

Red de Infraestructuras Geodésicas

Subdirección General de Astronomía y Geodesia

Reseña de Señal de Nivelación

11-abr-2026

Situación Geográfica:

Número: **931002**

Nombre: **NGR332®**

Línea o Ramal: **931. Línea Anaga - Tres de Mayo**

Municipio: Santa Cruz de Tenerife

Provincia: Santa Cruz de Tenerife (Isla de Tenerife)

Hoja MTN50: 1090

Señal: Principal **En posición:** Vertical

Señalizada: 01 de mayo de 1983

Nivelada: 01 de enero de 2003

Enlaces:

Anterior: 931001 - SSC5

Posterior: 931003 - SSC6

Agrupada con: 1931001 - NAPH407.

Datos Geodésicos:

Altitud ortométrica: 52,7189 m.

Geopotencial: 51,6324 u.g.p.

Gravedad en superficie: 979388,87 mgals. *Observada*

Cálculo:



Coordenadas GeogrA¡ficas REGCAN95:

SEÑAL DESAPARECIDA

2024-04-13: Desaparecido.

Longitud: - 16° 15' 19"

Latitud: 28° 29' 19"

Altitud elipsoidal:

Precisión: ± (1 m - 10 m.)

Reseña:

Situada en la población de Santa Cruz de Tenerife, sobre el murete que bordea el Parque Municipal y al lado N. de la escalinata de entrada por la calle Numancia, según croquis.

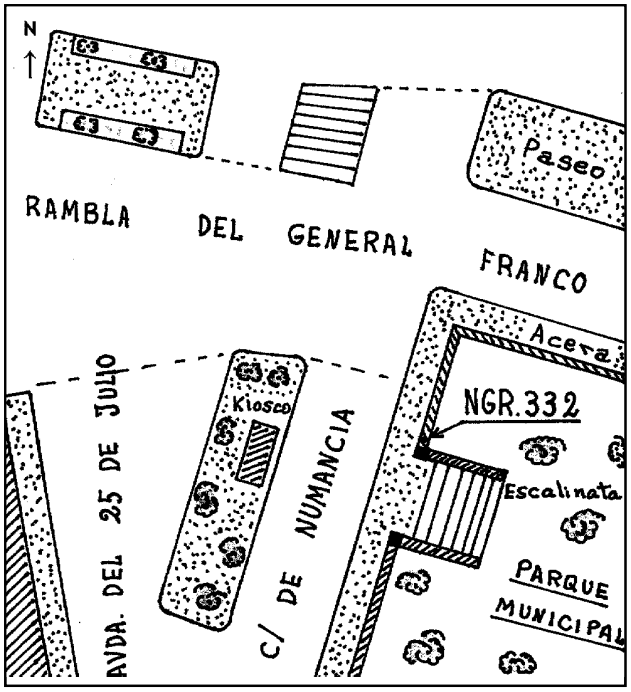

Observaciones:

Informe del estado de la Señal en: InfoRN.pdf

GOBIERNO DE ESPAÑA | MINISTERIO DE TRANSPORTES Y MOVILIDAD SOSTENIBLE | INSTITUTO GEOGRÁFICO NACIONAL

Red de Infraestructuras Geodésicas

Subdirección General de Astronomía y Geodesia

Reseña de Señal de Nivelación

11-abr-2026

Situación Geográfica:

Número: **931003**

Nombre: **SSC6**

Línea o Ramal: **931. Línea Anaga - Tres de Mayo**

Municipio: Santa Cruz de Tenerife

Provincia: Santa Cruz de Tenerife (Isla de Tenerife)

Hoja MTN50: 1090

Señal: Secundaria **En posición:** Vertical

Señalizada: 01 de mayo de 1983

Nivelada: 01 de enero de 2003

Datos Geodésicos:

Altitud ortométrica: 62,3199 m.

Geopotencial: 61,0355 u.g.p.

Gravedad en superficie: 979386,13 mgals. *Observada*

Cálculo:

Coordenadas GeogrÃ¡ficas REGCAN95:

Longitud: - 16° 15' 35"

Latitud: 28° 28' 11"

Altitud elipsoidal:

Precisión: ± (1 m - 10 m.)

Reseña:

Situada en la población de Santa Cruz de Tenerife, sobre el extremo N. del primer peldaño de acceso a la Plaza de Toros por la puerta de la Rambla del General Franco, según croquis.

Observaciones:

Informe del estado de la Señal en: InfoRN.pdf

Enlaces:

Anterior: 931002 - NGR332®

Posterior: 931004 - SSC7

Agrupada con:

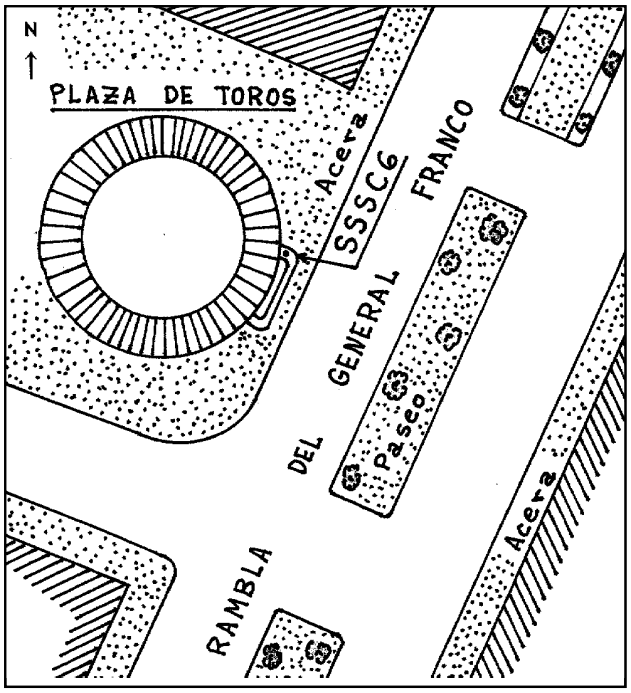

GOBIERNO DE ESPAÑA | MINISTERIO DE TRANSPORTES Y MOVILIDAD SOSTENIBLE | INSTITUTO GEOGRÁFICO NACIONAL

Red de Infraestructuras Geodésicas

Subdirección General de Astronomía y Geodesia

Reseña de Señal de Nivelación

11-abr-2026

Situación Geográfica:

Número: **931004**

Nombre: **SSC7**

Línea o Ramal: **931. Línea Anaga - Tres de Mayo**

Municipio: Santa Cruz de Tenerife

Provincia: Santa Cruz de Tenerife (Isla de Tenerife)

Hoja MTN50: 1090

Señal: Secundaria **En posición:** Vertical

Señalizada: 01 de mayo de 1983

Nivelada: 01 de enero de 2003

Enlaces:

Anterior: 931003 - SSC6

Posterior: 931005 - SSC8

Agrupada con:

Datos Geodésicos:

Altitud ortométrica: 72,8529 m.

Geopotencial: 71,3511 u.g.p.

Gravedad en superficie: 979381,98 mgals. *Observada*

Cálculo:

Coordenadas GeogrA¡ficas REGCAN95:

SEÑAL DESAPARECIDA

2024-04-13: Desaparecido.

Longitud: - 16° 15' 44"

Latitud: 28° 27' 52"

Altitud elipsoidal:

Precisión: ± (1 m - 10 m.)



Reseña:

Situada en la población de Santa Cruz de Tenerife, sobre la acera de la puerta de entrada al Parque Cultural, al lado S. de la misma, según croquis.

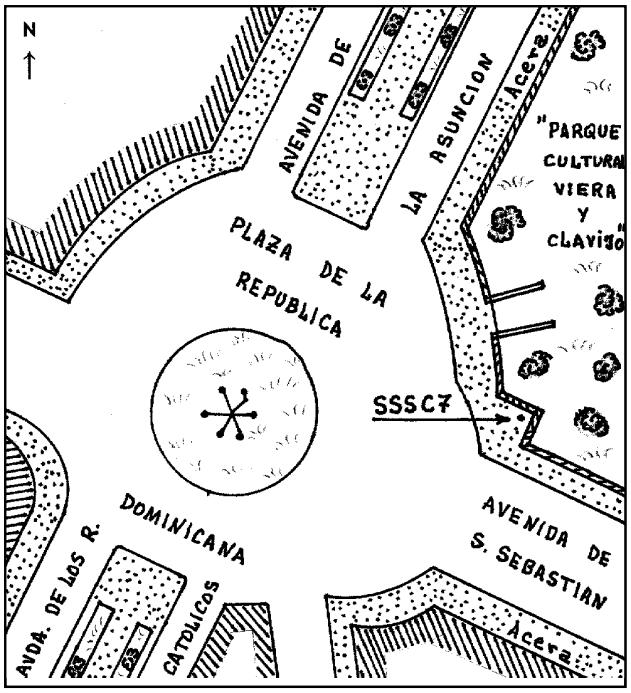

Observaciones:

Informe del estado de la Señal en: InfoRN.pdf

GOBIERNO DE ESPAÑA | MINISTERIO DE TRANSPORTES Y MOVILIDAD SOSTENIBLE | INSTITUTO GEOGRÁFICO NACIONAL

Red de Infraestructuras Geodésicas

Subdirección General de Astronomía y Geodesia

Reseña de Señal de Nivelación

11-abr-2026

Situación Geográfica:

Número: **931005**

Nombre: **SSC8**

Línea o Ramal: **931. Línea Anaga - Tres de Mayo**

Municipio: Santa Cruz de Tenerife

Provincia: Santa Cruz de Tenerife (Isla de Tenerife)

Hoja MTN50: 1090

Señal: Secundaria **En posición:** Vertical

Señalizada: 01 de mayo de 1983

Nivelada: 01 de enero de 2003

Enlaces:

Anterior: 931004 - SSC7

Posterior: 932 - NGR328 (Tres de Mayo)*

Agrupada con:

Datos Geodésicos:

Altitud ortométrica: 75,2698 m.

Geopotencial: 73,7179 u.g.p.

Gravedad en superficie: 979379,1 mgals. *Observada*

Cálculo:

Coordenadas GeogrA¡ficas REGCAN95:

SEÑAL DESAPARECIDA

2024-04-13: Desaparecido.

Longitud: - 16° 15' 50"

Latitud: 28° 27' 33"

Altitud elipsoidal:

Precisión: ± (1 m - 10 m.)

Reseña:

Situada en la población de Santa Cruz de Tenerife, sobre la acera de un cruce de calles y junto a una farola de alumbrado, al E. de la Avda. de los Reyes Católicos, según croquis.

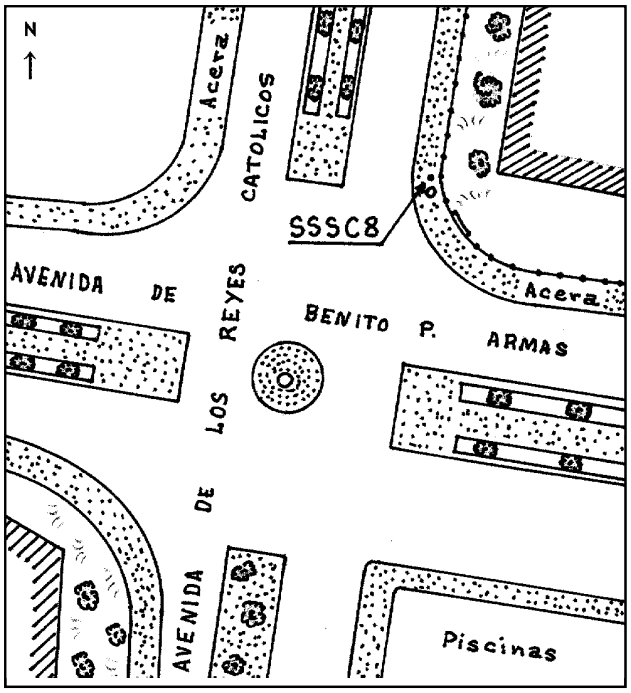

Observaciones:

Informe del estado de la Señal en: InfoRN.pdf