GOBIERNO DE ESPAÑA | MINISTERIO DE TRANSPORTES Y MOVILIDAD SOSTENIBLE | INSTITUTO GEOGRÁFICO NACIONAL

Red de Infraestructuras Geodésicas

Subdirección General de Astronomía y Geodesia

Reseña de Señal de Nivelación

11-abr-2026

Situación Geográfica:

Número: **933001**

Nombre: **NGR327**

Línea o Ramal: **933. Línea Tres de Mayo - Autopistas**

Municipio: Santa Cruz de Tenerife

Provincia: Santa Cruz de Tenerife (Isla de Tenerife)

Hoja MTN50: 1090

Señal: Principal **En posición:** Vertical

Señalizada: 01 de mayo de 1983

Nivelada: 01 de enero de 2003

Enlaces:

Anterior: 932 - NGR328 (Tres de Mayo)*

Posterior: 933002 - SS1

Agrupada con: 932 - NGR328 (Tres de Mayo)*.

Datos Geodésicos:

Altitud ortométrica: 84,3081 m.

Geopotencial: 82,5697 u.g.p.

Gravedad en superficie: 979376,31 mgals. *Observada*

Cálculo:

Coordenadas GeogrA¡ficas REGCAN95:

SEÑAL DESAPARECIDA

2024-04-17: Desaparecido.

Longitud: - 16° 16' 01"

Latitud: 28° 27' 22"

Altitud elipsoidal:

Precisión: ± (1 m - 10 m.)

Reseña:

Situada en la población de Santa Cruz de Tenerife, sobre el extremo O. de la imposta de un puente sobre un paso inferior y al S. de la desviación hacia la Avda. Tres de Mayo, según croquis.

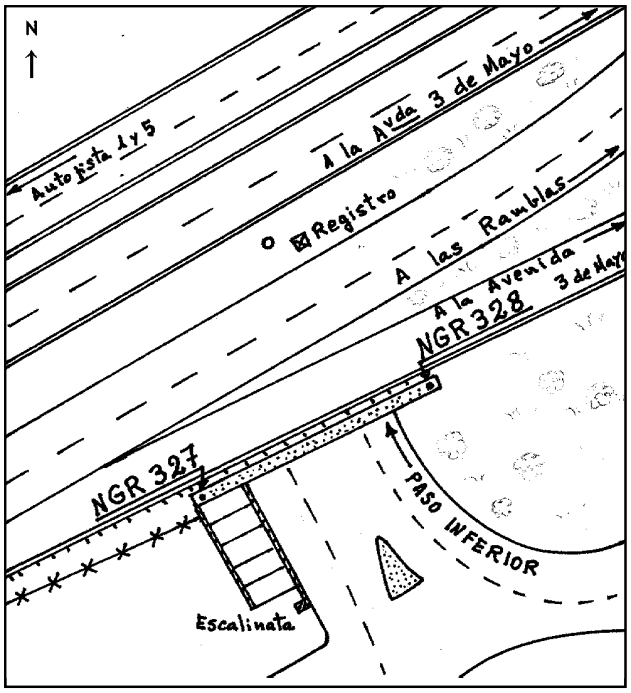

Observaciones:

Informe del estado de la Señal en: InfoRN.pdf

GOBIERNO DE ESPAÑA | MINISTERIO DE TRANSPORTES Y MOVILIDAD SOSTENIBLE | INSTITUTO GEOGRÁFICO NACIONAL

Red de Infraestructuras Geodésicas

Subdirección General de Astronomía y Geodesia

Reseña de Señal de Nivelación

11-abr-2026

Situación Geográfica:

Número: **933002**

Nombre: **SS1**

Línea o Ramal: **933. Línea Tres de Mayo - Autopistas**

Municipio: Santa Cruz de Tenerife

Provincia: Santa Cruz de Tenerife (Isla de Tenerife)

Hoja MTN50: 1090

Señal: Secundaria **En posición:** Vertical

Señalizada: 01 de mayo de 1983

Nivelada: 01 de enero de 2003

Datos Geodésicos:

Altitud ortométrica: 105,2885 m.

Geopotencial: 103,1169 u.g.p.

Gravedad en superficie: 979369,81 mgals. *Observada*

Cálculo:

Coordenadas GeogrÃ¡ficas REGCAN95:

Longitud: - 16° 16' 17"

Latitud: 28° 27' 06"

Altitud elipsoidal:

Precisión: ± (1 m - 10 m.)

Reseña:

Situada en el Km. 1,050 de la autopista TF-1, sobre el extremo N. de la solera de la cuneta hormigonada y al E. de la autopista, según croquis.

Observaciones:

Informe del estado de la Señal en: InfoRN.pdf

Enlaces:

Anterior: 933001 - NGR327

Posterior: 933003 - SS1.6

Agrupada con:

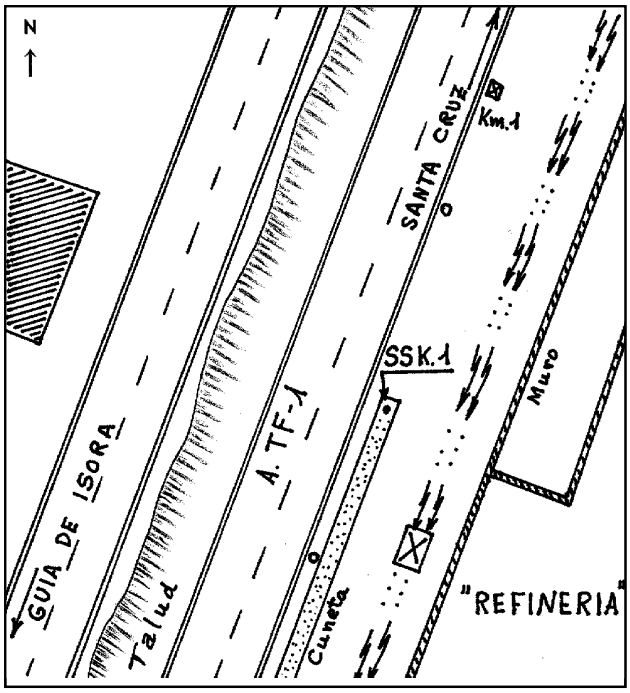

GOBIERNO DE ESPAÑA | MINISTERIO DE TRANSPORTES Y MOVILIDAD SOSTENIBLE | INSTITUTO GEOGRÁFICO NACIONAL

Red de Infraestructuras Geodésicas

Subdirección General de Astronomía y Geodesia

Reseña de Señal de Nivelación

11-abr-2026

Situación Geográfica:

Número: **933003**

Nombre: **SS1.6**

Línea o Ramal: **933. Línea Tres de Mayo - Autopistas**

Municipio: Santa Cruz de Tenerife

Provincia: Santa Cruz de Tenerife (Isla de Tenerife)

Hoja MTN50: 1090

Señal: Secundaria **En posición:** Vertical

Señalizada: 01 de mayo de 1983

Nivelada: 01 de enero de 2003

Datos Geodésicos:

Altitud ortométrica: 118,7142 m.

Geopotencial: 116,2651 u.g.p.

Gravedad en superficie: 979364,31 mgals. *Observada*

Cálculo:

Coordenadas GeogrÃ¡ficas REGCAN95:

Longitud: - 16° 16' 28,6600"

Latitud: 28° 26' 49,9600"

Altitud elipsoidal: 163,053 m.

Precisión: ± (0,05m - 0,1 m.)

Reseña:

Situada en el Km. 1,600 de la autopista TF-1, sobre el extremo N. de un muro de contención y al E. de la autopista, según croquis.

Observaciones:

Informe del estado de la Señal en: InfoRN.pdf

Enlaces:

Anterior: 933002 - SS1

Posterior: 933 - NGR326 (Autopistas)*
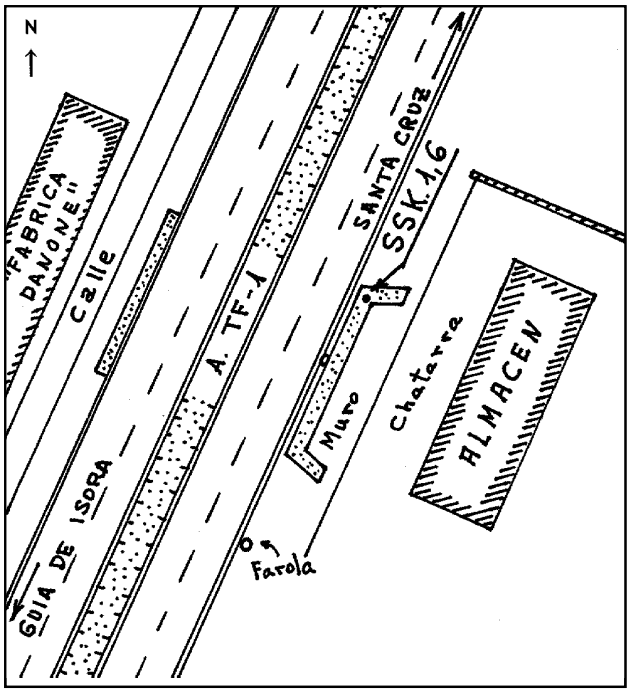
Agrupada con: