GOBIERNO DE ESPAÑA | MINISTERIO DE TRANSPORTES Y MOVILIDAD SOSTENIBLE | INSTITUTO GEOGRÁFICO NACIONAL

Red de Infraestructuras Geodésicas

Subdirección General de Astronomía y Geodesia

Reseña de Señal de Nivelación

11-abr-2026

Situación Geográfica:

Número: **939001**

Nombre: **SSK1'4**

Línea o Ramal: **939. Cruce de Güimar - Güimar**

Municipio: Güímar

Provincia: Santa Cruz de Tenerife (Isla de Tenerife)

Hoja MTN50: 1092

Señal: Secundaria **En posición:** Vertical

Señalizada: 25 de octubre de 2005

Nivelada: 01 de enero de 2003

Enlaces:

Anterior: 937 - NGR299* (Cruce de Güímar)

Posterior: 939002 - SSK2'250

Agrupada con:

Datos Geodésicos:

Altitud ortométrica: 125,7641 m.

Geopotencial: 123,1707 u.g.p.

Gravedad en superficie: 979373,55 mgals. *Observada*

Cálculo:

Coordenadas GeogrA¡ficas REGCAN95:

SEÑAL DESAPARECIDA

Longitud: - 16° 23' 23,5171"

Latitud: 28° 18' 29,7908"

2024-04-16: Desaparecido.

Altitud elipsoidal: 172,087 m.

Precisión: ± 0,05 m.

Reseña:

En la margen sur, izquierda sentido Güímar, de la carretera TF-61, en el p.k. 1'400, en el extremo este del paso de cuneta de una casa (Ma&Lor-Bar Cafetería), a 1'20 metros de la raya blanca, según croquis. Dista unos 550 metros del Nodo 937 "Cruce de Güímar".

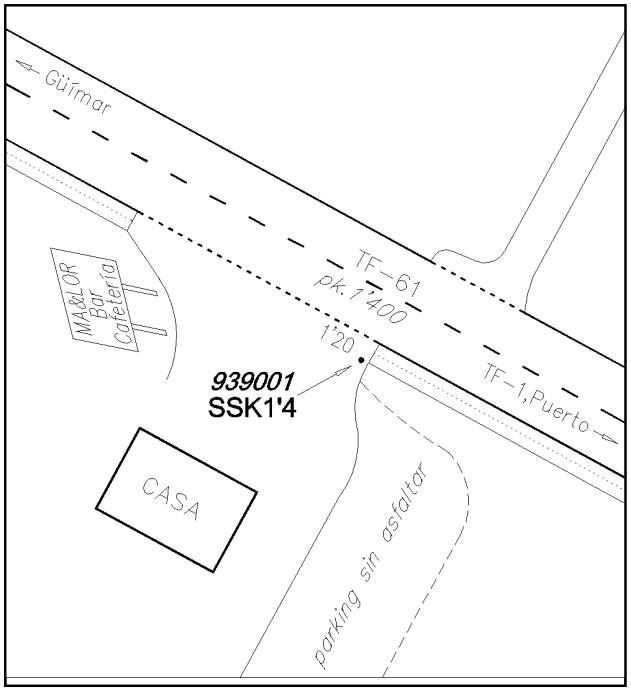

Observaciones:

Informe del estado de la Señal en: InfoRN.pdf

GOBIERNO DE ESPAÑA | MINISTERIO DE TRANSPORTES Y MOVILIDAD SOSTENIBLE | INSTITUTO GEOGRÁFICO NACIONAL

Red de Infraestructuras Geodésicas

Subdirección General de Astronomía y Geodesia

Reseña de Señal de Nivelación

11-abr-2026

Situación Geográfica:

Número: **939002**

Nombre: **SSK2'250**

Línea o Ramal: **939. Cruce de Güimar - Güimar**

Municipio: Güímar

Provincia: Santa Cruz de Tenerife (Isla de Tenerife)

Hoja MTN50: 1092

Señal: Secundaria **En posición:** Vertical

Señalizada: 25 de octubre de 2005

Nivelada: 01 de enero de 2003

Enlaces:

Anterior: 939001 - SSK1'4

Posterior: 939003 - SSK3'150

Agrupada con:

Datos Geodésicos:

Altitud ortométrica: 173,8134 m.

Geopotencial: 170,2279 u.g.p.

Gravedad en superficie: 979364,64 mgals. *Observada*

Cálculo:

Coordenadas GeogrA¡ficas REGCAN95:

SEÑAL DESAPARECIDA

Longitud: - 16° 23' 47,4325"

Latitud: 28° 18' 12,6422"

2024-04-16: Desaparecido.

Altitud elipsoidal: 219,713 m.

Precisión: ± 0,05 m.

Reseña:

En la margen sur, izquierda sentido Güímar, de la carretera TF-61, en el p.k. 2'250, en el extremo este del paso de cuneta de una finca de frutales, según croquis.

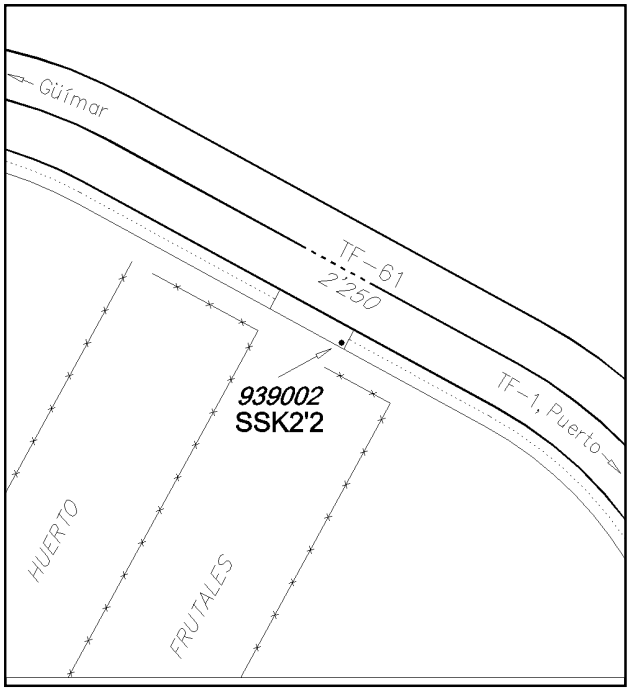

Observaciones:

Informe del estado de la Señal en: InfoRN.pdf

GOBIERNO DE ESPAÑA | MINISTERIO DE TRANSPORTES Y MOVILIDAD SOSTENIBLE | INSTITUTO GEOGRÁFICO NACIONAL

Red de Infraestructuras Geodésicas

Subdirección General de Astronomía y Geodesia

Reseña de Señal de Nivelación

11-abr-2026

Situación Geográfica:

Número: **939003**

Nombre: **SSK3'150**

Línea o Ramal: **939. Cruce de Güimar - Güimar**

Municipio: Güímar

Provincia: Santa Cruz de Tenerife (Isla de Tenerife)

Hoja MTN50: 1092

Señal: Secundaria **En posición:** Vertical

Señalizada: 25 de octubre de 2005

Nivelada: 01 de enero de 2003

Datos Geodésicos:

Altitud ortométrica: 221,1426 m.

Geopotencial: 216,5796 u.g.p.

Gravedad en superficie: 979356,53 mgals. *Observada*

Cálculo:

Coordenadas GeogrÃ¡ficas REGCAN95:

Longitud: - 16° 24' 14,2571"

Latitud: 28° 18' 46,8650"

Altitud elipsoidal: 266,885 m.

Precisión: ± 0,05 m.

Reseña:

En la margen sur, izquierda sentido Güímar, de la carretera TF-61, en el p.k. 3'150, cerca de la esquina noreste del cementerio de dicha población, sobre el bordillo de la acera, en el centro del tramo curvo, según croquis.

Observaciones:

Informe del estado de la Señal en: InfoRN.pdf

Enlaces:

Anterior: 939002 - SSK2'250

Posterior: 939004 - SSK3'9

Agrupada con:



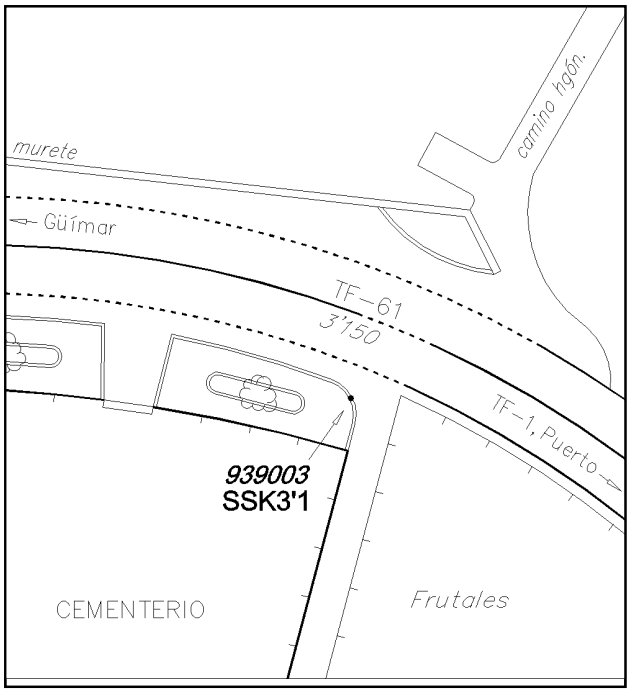

GOBIERNO DE ESPAÑA | MINISTERIO DE TRANSPORTES Y MOVILIDAD SOSTENIBLE | INSTITUTO GEOGRÁFICO NACIONAL

Red de Infraestructuras Geodésicas

Subdirección General de Astronomía y Geodesia

Reseña de Señal de Nivelación

11-abr-2026

Situación Geográfica:

Número: **939004**

Nombre: **SSK3'9**

Línea o Ramal: **939. Cruce de Güimar - Güimar**

Municipio: Güímar

Provincia: Santa Cruz de Tenerife (Isla de Tenerife)

Hoja MTN50: 1092

Señal: Secundaria **En posición:** Vertical

Señalizada: 25 de octubre de 2005

Nivelada: 01 de enero de 2003

Datos Geodésicos:

Altitud ortométrica: 267,6167 m.

Geopotencial: 262,0926 u.g.p.

Gravedad en superficie: 979346,8 mgals. *Observada*

Cálculo:

Coordenadas GeogrÃ¡ficas REGCAN95:

Longitud: - 16° 24' 38,2031"

Latitud: 28° 18' 45,8831"

Altitud elipsoidal: 313,906 m.

Precisión: ± 0,05 m.

Reseña:

En la margen norte, derecha sentido Güímar, de la carretera TF-61, en el p.k. 3'950, dentro de la población citada, antes del cruce donde existe una gasolinera Shell, frente al edifício de la Sociedad de Aguas Río y Badajoz, en línea con el borde este de un paso de peatones, sobre el bordillo de la acera, según croquis. Dista unos 200 metros del nodo 948 "Güimar".

Observaciones:

Informe del estado de la Señal en: InfoRN.pdf

Enlaces:

Anterior: 939003 - SSK3'150

Posterior: 948 - NGZ520* (Güímar)
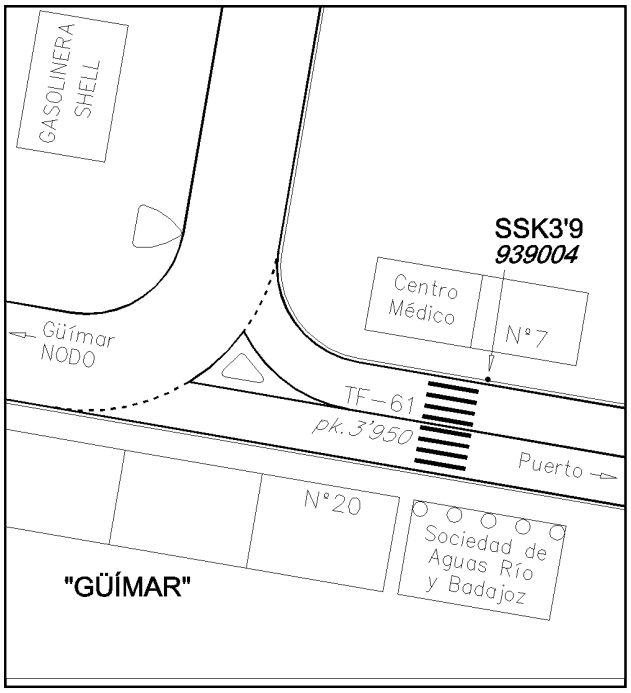
Agrupada con: 948 - NGZ520* (Güímar), 940001 - NGZ521.