GOBIERNO DE ESPAÑA | MINISTERIO DE TRANSPORTES Y MOVILIDAD SOSTENIBLE | INSTITUTO GEOGRÁFICO NACIONAL

Red de Infraestructuras Geodésicas

Subdirección General de Astronomía y Geodesia

Reseña de Señal de Nivelación

11-abr-2026

Situación Geográfica:

Número: **946001**

Nombre: **SS.Madre**

Línea o Ramal: **946. Cementerio Realejo Alto - Zamora Baja**

Municipio: Los Realejos

Provincia: Santa Cruz de Tenerife (Isla de Tenerife)

Hoja MTN50: 1092

Señal: Secundaria **En posición:** Vertical

Señalizada: 18 de noviembre de 2005

Nivelada: 01 de enero de 2003

Datos Geodésicos:

Altitud ortométrica: 341,1426 m.

Geopotencial: 334,099 u.g.p.

Gravedad en superficie: 979338,54 mgals. *Observada*

Cálculo:

Coordenadas GeogrÃ¡ficas REGCAN95:

Longitud: - 16° 35' 03,5"

Latitud: 28° 22' 49,6"

Altitud elipsoidal: 394 m.

Precisión: ± (0,1 m - 1 m.)

Reseña:

Desde el Nodo 949, situado en el Cementerio de Realejos Alto, se baja a la carretera TF-324 que se coge hacia la izquierda. A los 550 metros, entrando en zona urbana, se deja a la derecha la carretera TF-333 (La Zamora Alta y La Montañeta) y se continúa 50 metros más. En este punto, se toma a la derecha y descendiendo por la Calle La Gomera otros 50 metros, se llega a una isleta con una escultura dedicada "A La Madre". La señal se encuentra en el lado oeste del monumento, sobre el bordillo, según croquis.

Observaciones:

Informe del estado de la Señal en: InfoRN.pdf

Enlaces:

Anterior: 949 - NGZ371 (Cementerio Realejo Alto)

Posterior: 946002 - SS.Mancomunidad

Agrupada con:

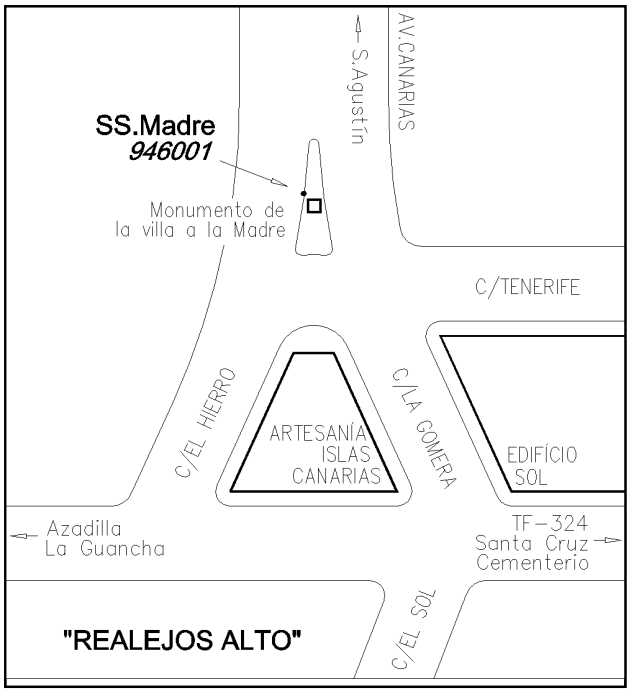

GOBIERNO DE ESPAÑA | MINISTERIO DE TRANSPORTES Y MOVILIDAD SOSTENIBLE | INSTITUTO GEOGRÁFICO NACIONAL

Red de Infraestructuras Geodésicas

Subdirección General de Astronomía y Geodesia

Reseña de Señal de Nivelación

11-abr-2026

Situación Geográfica:

Número: **946002**

Nombre: **SS.Mancomunidad**

Línea o Ramal: **946. Cementerio Realejo Alto - Zamora Baja**

Municipio: Los Realejos

Provincia: Santa Cruz de Tenerife (Isla de Tenerife)

Hoja MTN50: 1092

Señal: Secundaria **En posición:** Vertical

Señalizada: 18 de noviembre de 2005

Nivelada: 01 de enero de 2003

Datos Geodésicos:

Altitud ortométrica: 279,3562 m.

Geopotencial: 273,5911 u.g.p.

Gravedad en superficie: 979351,3 mgals. *Observada*

Cálculo:

Coordenadas GeogrÃ¡ficas REGCAN95:

Longitud: - 16° 35' 03,0341"

Latitud: 28° 23' 06,4701"

Altitud elipsoidal: 326,070 m.

Precisión: ± 0,05 m.

Reseña:

Desde la señal anterior, descendiendo por la Avenida de Canarias y recorridos unos 550 metros, se llega a un cruce que por la izquierda da acceso al edifício de la Mancomunidad del Norte de Tenerife. La señal se encuentra en el primer acceso peatonal a un parking en superfície, en el lado izquierdo entrando, sobre el bordillo a ras de suelo y al pié del murete que contiene las barandillas, según croquis.

Observaciones:

Informe del estado de la Señal en: InfoRN.pdf

Enlaces:

Anterior: 946001 - SS.Madre

Posterior: 946003 - SS.Foguetero

Agrupada con:

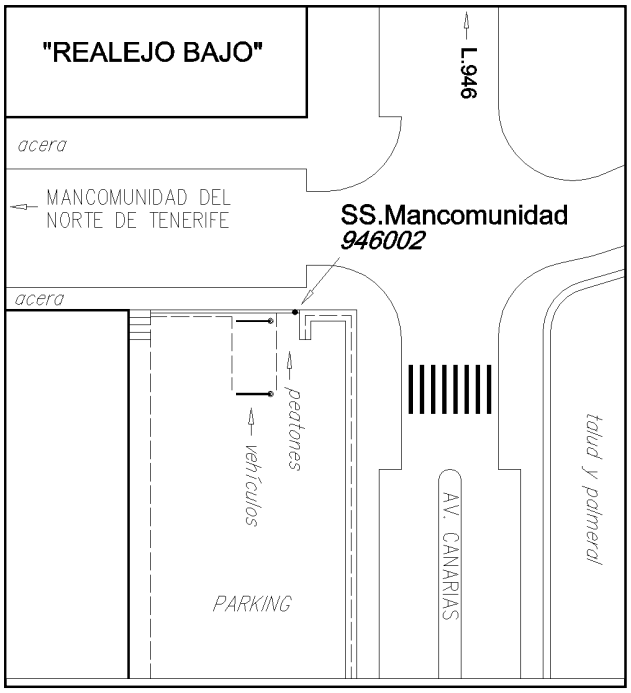

GOBIERNO DE ESPAÑA | MINISTERIO DE TRANSPORTES Y MOVILIDAD SOSTENIBLE | INSTITUTO GEOGRÁFICO NACIONAL

Red de Infraestructuras Geodésicas

Subdirección General de Astronomía y Geodesia

Reseña de Señal de Nivelación

11-abr-2026

Situación Geográfica:

Número: **946003**

Nombre: **SS.Foguetero**

Línea o Ramal: **946. Cementerio Realejo Alto - Zamora Baja**

Municipio: Los Realejos

Provincia: Santa Cruz de Tenerife (Isla de Tenerife)

Hoja MTN50: 1092

Señal: Secundaria **En posición:** Vertical

Señalizada: 18 de noviembre de 2005

Nivelada: 01 de enero de 2003

Enlaces:

Anterior: 946002 - SS.Mancomunidad

Posterior: 946004 - SS.Altesa

Agrupada con:

Datos Geodésicos:

Altitud ortométrica: 234,4080 m.

Geopotencial: 229,5723 u.g.p.

Gravedad en superficie: 979360,75 mgals. *Observada*

Cálculo:

Coordenadas GeogrA¡ficas REGCAN95:

SEÑAL DESAPARECIDA

2024-04-09: Desaparecido.

Longitud: - 16° 35' 03,0083"

Latitud: 28° 22' 18,6934"

Altitud elipsoidal: 281,061 m.

Precisión: ± 0,05 m.

Reseña:

Desde la señal anterior, descendiendo en dirección norte y recorridos unos 400 metros, se llega a la glorieta de intersección con la carretera TF-320, que en el lado este tiene una isleta con una estatua dedicada "Al Foguetero". La señal se encuentra sobre el vértice este del zócalo triangular del monumento, según croquis.

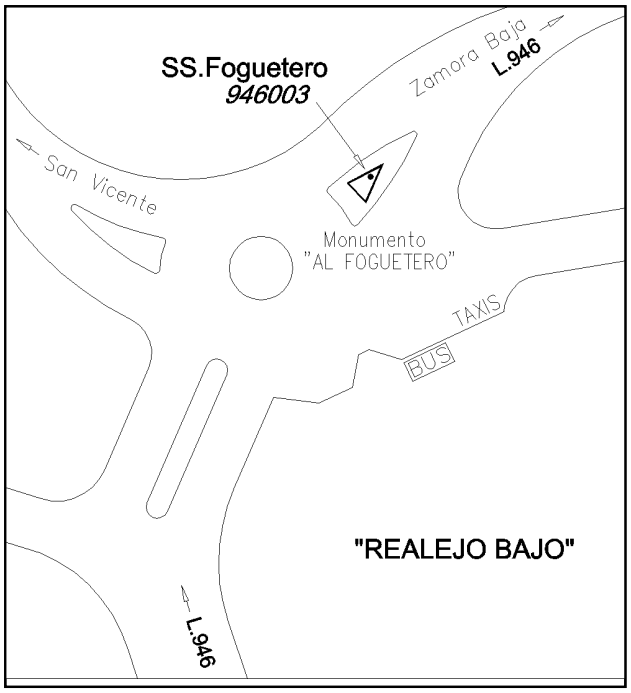

Observaciones:

Informe del estado de la Señal en: InfoRN.pdf

GOBIERNO DE ESPAÑA | MINISTERIO DE TRANSPORTES Y MOVILIDAD SOSTENIBLE | INSTITUTO GEOGRÁFICO NACIONAL

Red de Infraestructuras Geodésicas

Subdirección General de Astronomía y Geodesia

Reseña de Señal de Nivelación

11-abr-2026

Situación Geográfica:

Número: **946004**

Nombre: **SS.Altesa**

Línea o Ramal: **946. Cementerio Realejo Alto - Zamora Baja**

Municipio: Los Realejos

Provincia: Santa Cruz de Tenerife (Isla de Tenerife)

Hoja MTN50: 1092

Señal: Secundaria **En posición:** Vertical

Señalizada: 18 de noviembre de 2005

Nivelada: 01 de enero de 2003

Enlaces:

Anterior: 946003 - SS.Foguetero

Posterior: 946005 - NGZ574

Agrupada con:

Datos Geodésicos:

Altitud ortométrica: 219,5620 m.

Geopotencial: 215,0332 u.g.p.

Gravedad en superficie: 979364,47 mgals. *Observada*

Cálculo:

Coordenadas GeogrA¡ficas REGCAN95:

SEÑAL DESAPARECIDA

Longitud: - 16° 34' 43,5204"

2024-04-09: Desaparecido.

Latitud: 28° 22' 28,2622"

Altitud elipsoidal: 266,149 m.

Precisión: ± 0,05 m.

Reseña:

Desde la señal anterior, se coge hacia el este por la carretera TF-320 y recorridos unos 800 metros se llega a una glorieta de entronque con la autovía TF-5, donde hay un gran supermercado "ALTESA". La señal se encuentra sobre el extremo oeste del muro de contención separador de viales, donde comienza una bionda metálica, según croquis.

Observaciones:

Informe del estado de la Señal en: InfoRN.pdf

GOBIERNO DE ESPAÑA | MINISTERIO DE TRANSPORTES Y MOVILIDAD SOSTENIBLE | INSTITUTO GEOGRÁFICO NACIONAL

Red de Infraestructuras Geodésicas

Subdirección General de Astronomía y Geodesia

Reseña de Señal de Nivelación

11-abr-2026

Situación Geográfica:

Número: **946005**

Nombre: **NGZ574**

Línea o Ramal: **946. Cementerio Realejo Alto - Zamora Baja**

Municipio: Los Realejos

Provincia: Santa Cruz de Tenerife (Isla de Tenerife)

Hoja MTN50: 1092

Señal: Principal **En posición:** Horizontal

Señalizada: 18 de noviembre de 2005

Nivelada: 01 de enero de 2003

Datos Geodésicos:

Altitud ortométrica: 215,4192 m.

Geopotencial: 210,9761 u.g.p.

Gravedad en superficie: 979365,43 mgals. *Calculada*

Cálculo:

Coordenadas GeogrÃ¡ficas REGCAN95:

Longitud: - 16° 34' 34"

Latitud: 28° 23' 30"

Altitud elipsoidal:

Precisión: ± (1 m - 10 m.)

Reseña:

Desde la señal anterior, se pasa sobre la autovía TF-5 y en la glorieta se toma hacia el este por la carretera TF-320, que está indicada al Puerto de La Cruz. Recorridos unos 800 metros, 200 metros después de rebasar el km. 4, entronca por la izquierda un camino asfaltado (Nodo Zamora Baja). La señal, está un muro de contención alto (de una platanera), empotrada horizontalmente a 1'20 metros de su esquina este y a 1 metro sobre la rasante de la carretera, según croquis.

Observaciones:

Informe del estado de la Señal en: InfoRN.pdf

Enlaces:

Anterior: 946004 - SS.Altesa

Posterior: 938 - NGR171* (Zamora Baja)
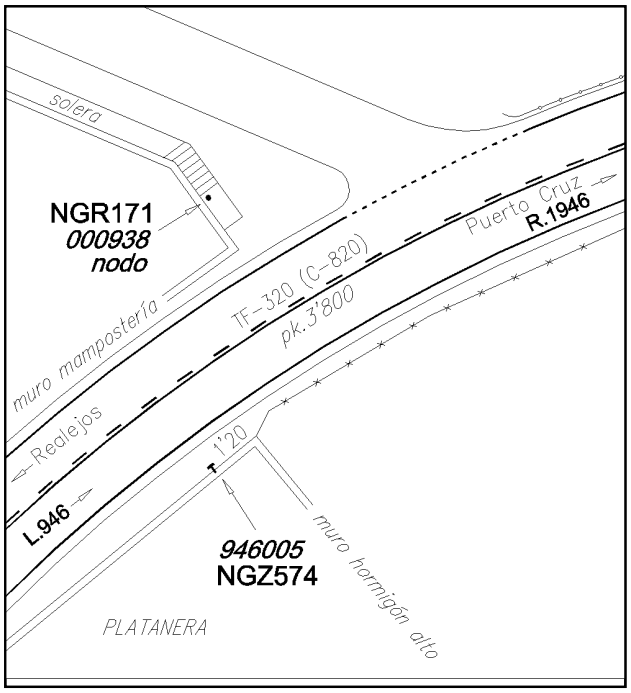
Agrupada con: 938 - NGR171* (Zamora Baja), 10936064 - NGR170.